COĞRAFİ BECERİLERİN DİJİTAL DÖNÜŞÜMÜ

Maarif Modeli ile Tam Uyum (Bütüncül Eğitim)

Oyunumuz, yeni müfredatın temel taşları olan şu kavramlar üzerine inşa edilmiştir:

Beceri Temelli Yaklaşım: Öğrenci bilgiyi ezberlemez; izohips verilerini kullanarak analiz yapar, sentezler ve sahada bir "eyleme" (soru çözümü/koordinat tespiti) dönüştürür.

Anlamlı Öğrenme: Soyut bir kavram olan yükselti eğrileri, Bergama'nın gerçek topografyası ve "2050 senaryosu" ile somutlaşır.

Erdem-Değer-Eylem Çerçevesi: Doğal çevreyi koruma, iklim değişikliği farkındalığı ve vatan coğrafyasını tanıma değerleri oyunun hikaye akışına yedirilmiştir.

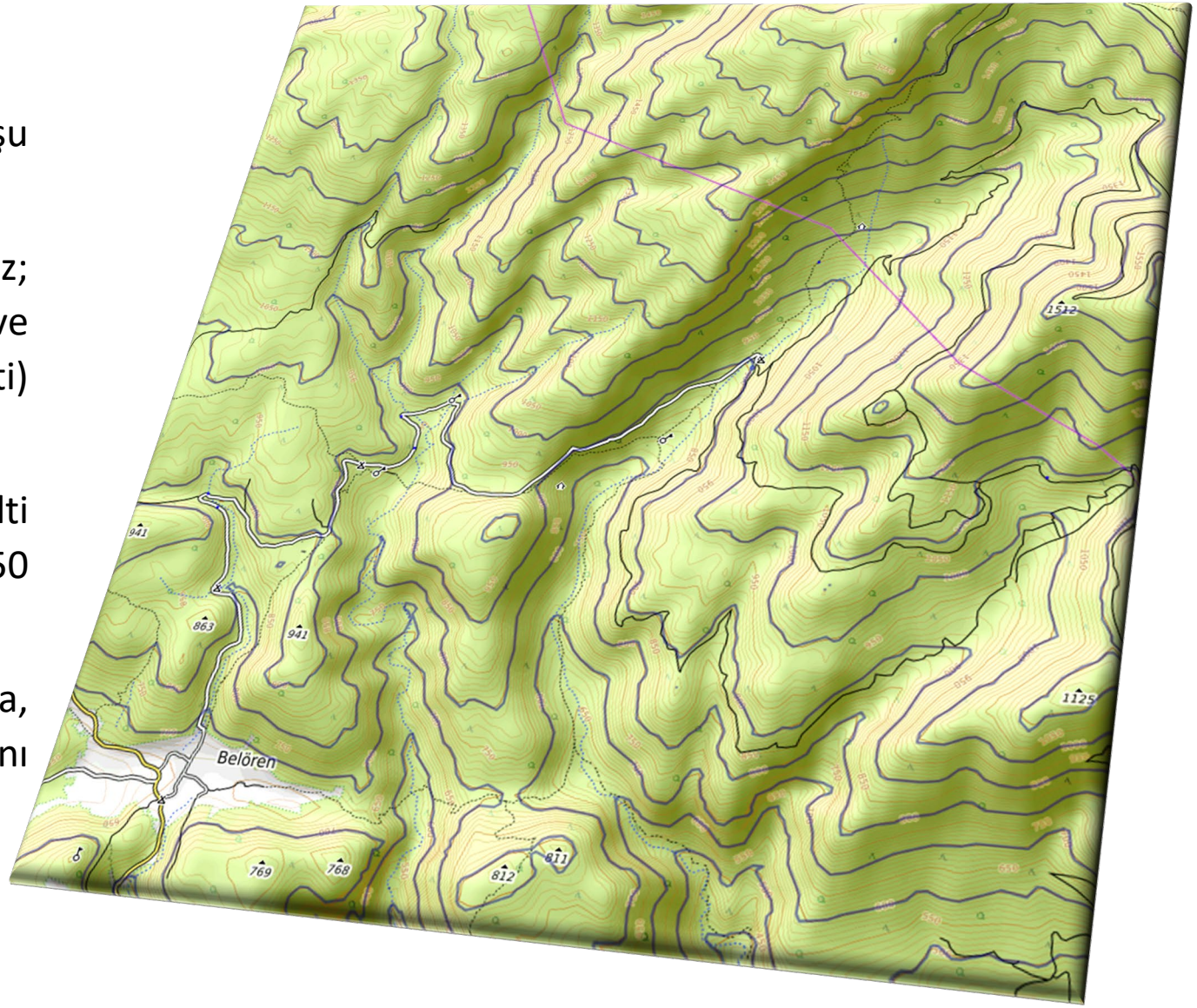

COĞRAFİ BECERİLERİN DİJİTAL DÖNÜŞÜMÜ

Eğitsel Değer: Mekânsal Düşünme Becerisi

İzohips Operasyonu, öğrencilere şu 21. yüzyıl yetkinliklerini kazandırır:

Görsel-Uzamsal Zekâ:

İki boyutlu haritalardan üç boyutlu profiller çıkarabilme.

Dijital Okuryazarlık:

Coğrafi Bilgi Sistemleri (CBS) mantığını kavrama.

Stratejik Karar Verme:

Sınırlı ipucu ve zamanla en doğru sonuca ulaşma.

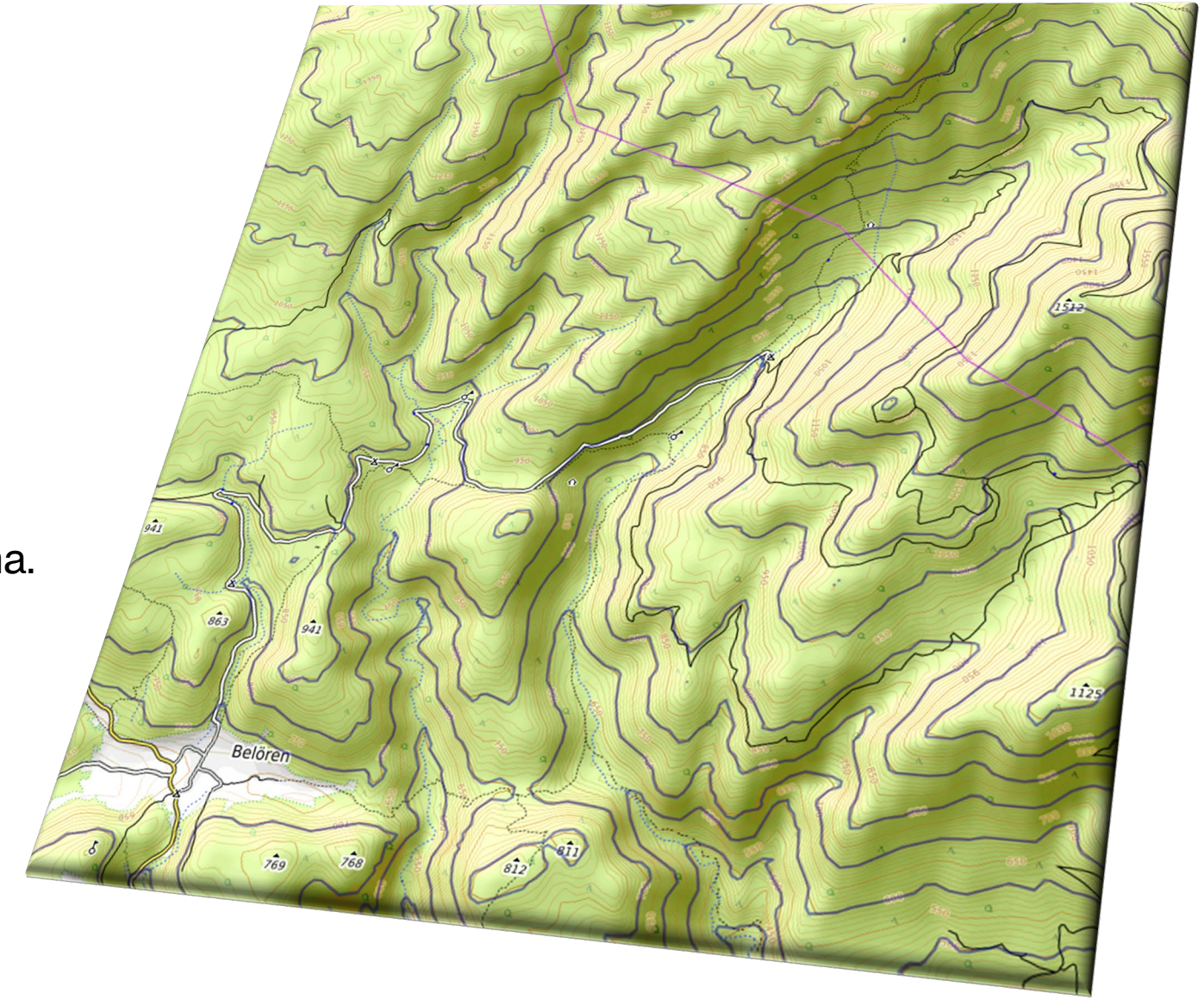

COĞRAFİ BECERİLERİN DİJİTAL DÖNÜŞÜMÜ

Nasıl Oynatılır?

Hazırlık: Excel dosyasına sınıf listenizi kopyalayınız. Dosyadaki eşleştir düğmesine (makrolara izin vermeniz gerekir.) basarak takımları oluşturunuz. Bu listeyi csv formatına çevirip karargah.html ye yükleyiniz

Brifing: "İntro Video"yu sınıfa izleterek hikaye akışını başlatınız.

Görev Başına: Videodan sonra takımları bilgisayar başına alınız.

Aktif Saha: Öğrenciler, "Saha Kılavuzu"ndaki teknik bilgilerden yararlanarak 10 kritik görevi tamamlatınız.

Değerlendirme: karargah.html üzerinden gelen anlık verilerle sınıf başarısını analiz ediniz ve "Görev Sonu Raporu" ile süreci taçlandırınız.
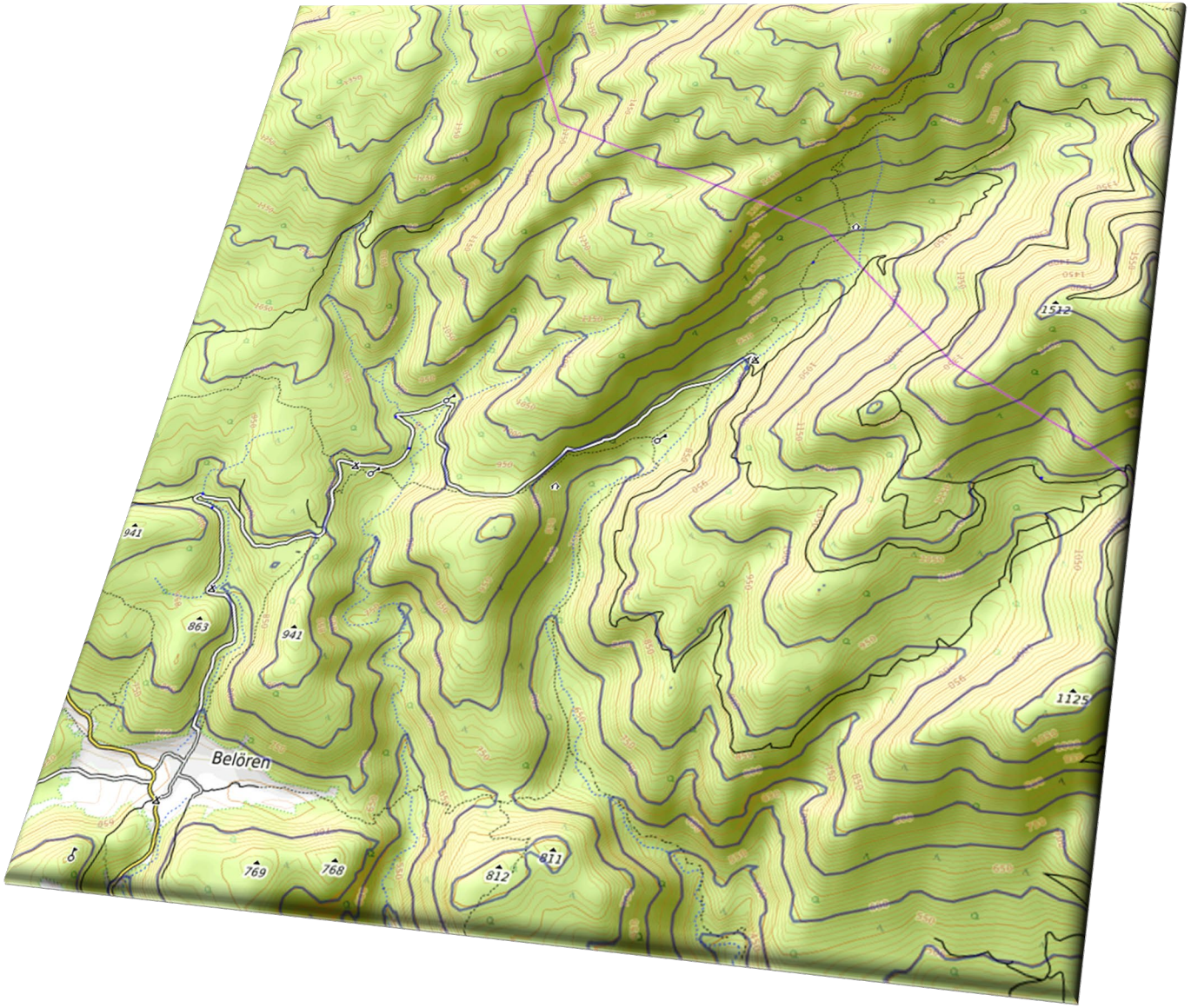
NOT: YEĞİTEK'in Yenilikçi Sınıfları için hazırlanmıştır.