Eş Yükselti Eğrisi (İzohips) Yöntemi

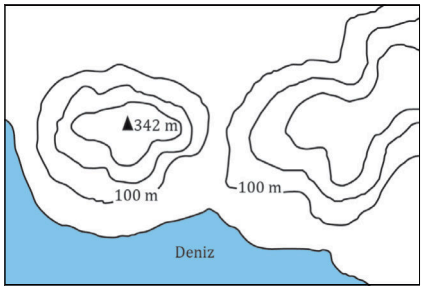

- Deniz seviyesinden itibaren aynı yükseltiye sahip noktaların birleştirilmesiyle elde edilen eğrilere izohips denir.
- Deniz seviyesinin altındaki alanlar da bu yöntemle gösterilebilir.
- Deniz ya da göllerde aynı derinliğe sahip noktaların birleştirilmesi ile elde edilen eğrilere eş derinlik eğrisi (izobat) denir.
- İzohips yöntemi, yeryüzü şekillerinin gösterilmesinde en yaygın kullanılan yöntemlerden biridir.

İzohipslerin Özellikleri

- İç içe çizilen kapalı eğrilerdir.
- En içteki eğri en yüksek yeri, en dıştaki eğri ise en alçak yeri gösterir (çukur alanlar hariç).
- Aynı izohips üzerindeki bütün noktaların yükselti değeri aynıdır.
- Kıyı çizgisi 0 (sıfır) metre ile gösterilir.
- 0 metre eğrisinden sonra gelen ilk eğrinin değeri izohipsler arası yükselti farkının ne kadar olduğunu gösterir.
- Eş yükselti eğrileri arası yükselti farkı (eküidistans değeri) eşittir. Eküidistans değeri, izohips haritasının ölçeğine bağlı olarak değişir
- Eğimin fazla olduğu yerlerde izohipsler sık, az olduğu yerlerde seyrek çizilir.
- Birbirini çevrelemeyen komşu iki izohipsin yükselti değeri aynıdır.
- Bir akarsuyun her iki tarafı aynı yükselti değeri ile başlar.
- Her eğri başka bir yüksekliği gösterdiği için birbirlerini kesmez.

İzohips Haritalarında Yer Şekillerinin Gösterilmesi

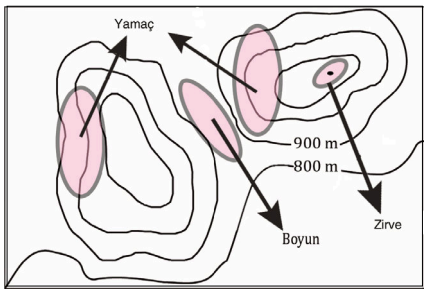

- Çevresine göre yüksekte kalan yerlere tepe, iki tepe arasında kalan alçak yerlere boyun denir.
- Vadi ve tepelerin kenarları ile sırtların her iki tarafında kalan kısımlarına yamaç adı verilir.
- Dağ ya da tepelerin en yüksek noktasına zirve (doruk) denir.Eş yükselti eğrilerinde zirve nokta(.) veya üçgen ile gösterilir.

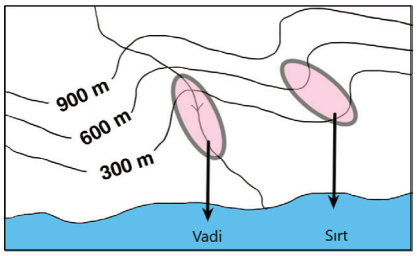

- Eğrilerin, yükseltinin arttığı yöne doğru yaptığı büklümler vadileri gösterir.
- Eğrilerin yükseltinin azaldığı yöne doğru yaptığı büklümler sırtları gösterir.

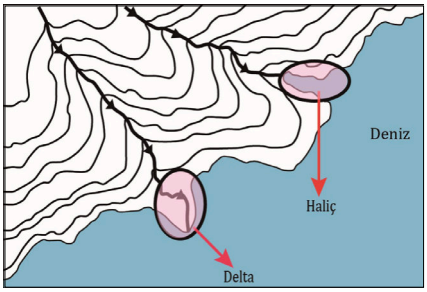

- Akarsuların taşıdığı alüvyonların akarsuların denize döküldüğü yerde birikmesi sonucu denize doğru çıkıntılar oluşur. Bu çıkıntılara delta denir.
- Deniz ve okyanus kıyılarında akarsuların denize döküldüğü ağız kısmının karaya doğru girintiler yaparak sularla dolmasıyla haliçler oluşur.

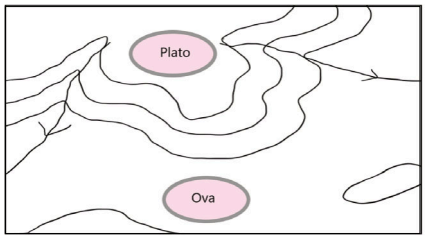

- Akarsular tarafından yarılmış, etrafına göre yüksekte kalan düzlüklere plato denir.
- Etrafına göre alçakta kalmış düz alanlara ova denir.

- İzohips haritalarında akarsu yatağı üzerinde izohipslerin birbirine çok yaklaşması eğimin arttığını ve şelale oluşumunu gösterir.
- İzohipslerin deniz kıyısında birbirine çok yaklaştığı yerler falez (yalıyar) oluşumunu gösterir.

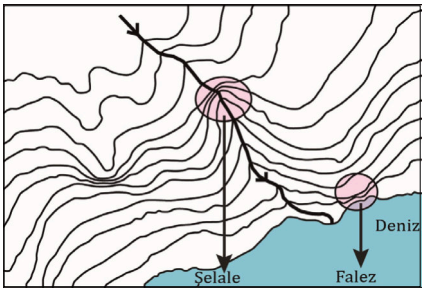

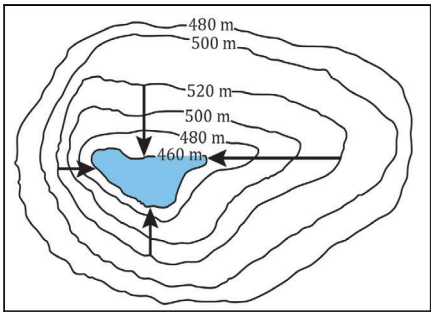

- Etrafına göre alçakta kalmış çukur alanlar içe dönük ok işaretiyle gösterilir.

Profil Çıkarma

Eş yükselti eğrileriyle oluşturulan izohips (topoğrafya) haritalarından profil çıkarma işlemi yapılabilir. Profil çıkarma işleminin aşamaları şunlardır:

- Profil çıkarılacak alan iki nokta ile belirlenir ve bu noktalar arasına bir doğru çizilir.

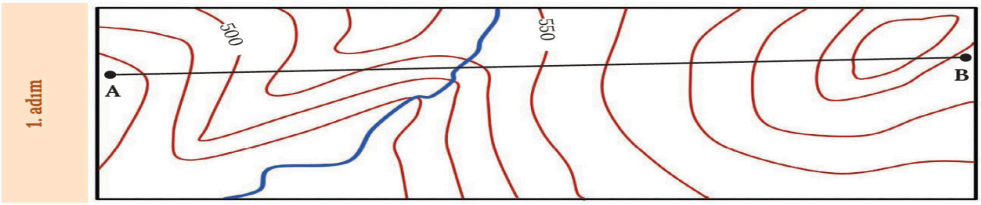

- Belirlenen doğrultudaki eş yükselti eğrilerinin yükselti değerleri bulunur.

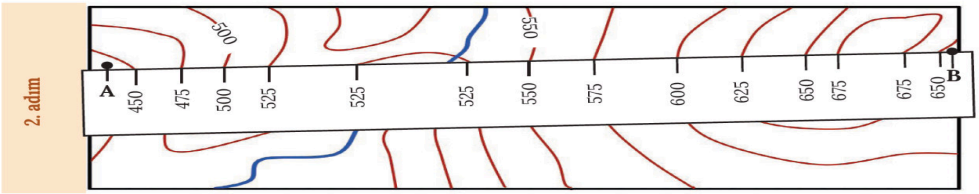
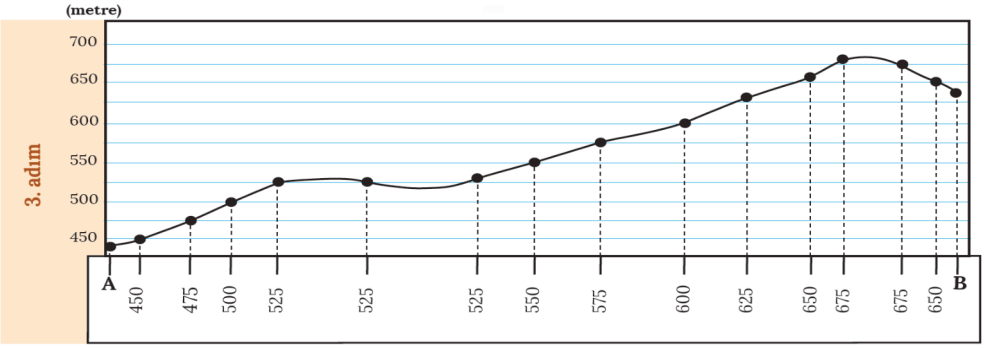
- Yükselti değerleri bulunan eş yükselti eğrilerinin yükseltilerine göre iz düşümleri alınır.
- İz düşümleri alınan noktalar birleştirilir.